Bogotá 27/11/2025

La orientación para organizar y restructurar el área de seguridad de una empresa de transporte de carga, debe ser de lineamientos integrales enfocados en la gestión y mitigación de los riesgos operacionales y la seguridad en la cadena de suministro con una visión óptica y de estricto cumplimiento con la normativa Colombiana vigente.

Para entender este contexto de gestión y enfoque de mitigación del riesgo es importante conocer el contexto país y la situación a la que se enfrenta el transporte por carretea en la actualidad en tal sentido me permito realizar las siguientes apreciaciones así;

EL AMBIENTE OPERACIONAL DE LA SEGURIDAD 2025 Y SU IMPACTO EN LAS OPERACIONES LOGISTICAS Y DEL TRANSPORTE TERRESTRE DE CARGA

APRECIACION DE SITUACION

1. Situación general.

- El ambiente socio económico y socio político de Colombia durante el lapso 2024 y sus efectos directos en el año 2025, están marcados por impacto social, político y económico.

- El contexto anterior, determinó un cambio en el comportamiento de las actividades ilícitas a nivel nacional. En general, de acuerdo con datos estadísticos 2024 de la PONAL, se apreció un descenso general en las modalidades delictivas del hurto a personas, residencias, comercios, bancos, motos y automóviles; así como también, un descenso en los asesinatos, pero la piratería terrestre (aumento en cifras globales nacionales teniendo como principal referencia los corredores de Bogotá - Buenaventura, Medellín y Barranquilla). Adicionalmente a esto, se apreció un aumento en las acciones delictivas de carácter terrorista; siendo estas últimas, las quemás atañen a las operaciones de seguridad de las operaciones logísticas y de transporte terrestre de carga. En este sentido se registró un incremento en los enfrentamientos armados en importantes sectores del territorio nacional entre grupos armados ilegales dedicados al narcotráfico, a la minería ilegal y a la extorsión (disidencias FARC, ELN, Clan del Golfo, carteles del narcotráfico, etc.), y entre estos y la fuerza pública.

  Estos enfrentamientos entre los mencionados grupos armados ilegales, están determinados por el control territorial de regiones geográficas claves de cultivos ilícitos, de producción de clorhidrato de cocaína y para el transporte hacia el exterior por estratégicos corredores de movilidad.

- Los combates por el control territorial en cuestión no solo implican el control geográfico en sí mismo para las actividades delictivas mencionadas; sino, que materializan graves hechos atentatorios contra los DD.HH. representados por asesinatos selectivos contra líderes comunitarios y líderes políticos locales, asesinatos múltiples o masacres en pequeños centros poblados y extorsión a la población civil (campesinos, pequeñas y medianas empresas); hechos estos, que han generado en este último 2024 y manteniéndose en el 2025, desplazamientos poblacionales forzados, severas restricciones a de la libre circulación en el territorio nacional, amenazantes paros armados declarados por estas estructuras armadas ilegales, secuestros y desapariciones con grave impacto social, político y económico. Esto último, no solo en el ámbito nacional, sino también con importantes repercusiones en el ámbito internacional.

- Es de fundamental consideración, el masivo flujo ilegal de la inmigración forzada de la población venezolana (hasta diciembre 2019: 1.9 millones de migrantes) como consecuencia de la tiranía implantada en esa nación con el impacto para la seguridad y defensa nacional:

  - Violación del territorio nacional.
  - Captación por los grupos armados ilegales.
  - Incremento de la delincuencia común en principales ciudades.
  - Presión sobre las instituciones colombianas, especialmente sanitarias.
  - Articulación con plataformas políticas de la extrema izquierda colombiana con fines desestabilizadores.
  - Crisis humanitaria.

- Al contexto anterior, hay que visualizar importantes aspectos de carácter económico que inciden en el ambiente operacional de la seguridad 2024 - 2025 a nivel nacional. Así, luego de un crecimiento económico de 1,4% en 2024, se registró un aumento al 3,3% en el 2025.

- la economía nacional en el año 2020 con hondas implicaciones para la seguridad a nivel nacional como consecuencia del detrimento laboral con un impacto negativo especialmente en el turismo, restaurantes, actividades de esparcimiento y compras a crédito (reducción de 22.000.000 a 18.000.000 empleos). Un simple reflejo de esta crítica situación es el hecho que en varias rutas nacionales se perpetraron saqueos a vehículos transportadores de alimentos; así como también, la conflictividad planteada al sector transportador por el incremento de los precios de los peajes en las rutas nacionales y de las regulaciones implementadas por el Ministerio de Transporte mediante el CICETAC herramienta que favorece plenamente a las empresas tenedoras de flota propia.

- A la par, el gobierno nacional reaccionó a la crisis adoptando medidas proteccionistas a favor de la población y para paliar la desaceleración de la economía en el 2023 y previendo un repunte de la economía para el 2024/2025:

  - Aporte de recursos adicionales (31 billones de pesos) para el sistema de salud.
  - Programas de emergencia: transferencias monetarias no condicionadas y devoluciónde IVA para población de bajos ingresos.
  - Suspensión de impuestos en sectores seleccionados.
  - Reducción arancelaria para las importaciones de medicamentos y equipos médicos.
  - Programa de ayudas para pago de nómina de pequeñas y medianas empresas.
  - Otorgamientos de créditos especiales para sectores especiales (70 billones de pesos).

- Sin duda, a la luz de los hechos, los actores más determinantes en el ambiente operacional de la seguridad 2025 a nivel nacional, lo constituyen los grupos armados ilegales o Grupos Armados Organizados (GAO). Estos actores sin duda, constituyen el factor más crítico en el ambiente operacional de la seguridad en el 2025, por la pugna entre ellos que materializan enfrentamientos armados para expandirse a los antiguos territorios FARC-EP, posterior al Acuerdo de Paz firmado por esa organización narcoterrorista, para el control territorial de regiones geográficas necesarias para mantener el dominio de las economías ilegales y para el transporte hacia el exterior por estratégicos corredores de movilidad. Estas estructuras armadas desarrollan varios tipos de economías ilegales a gran escala (minería ilegal de oro, coltán y uranio empobrecido, extorsión, secuestros, etc.) para no depender solamente del narcotráfico y permitiéndoles expandirse geográficamente. Incluso, en muchos casos su accionar es conjunto especialmente en las zonas fronterizas con Venezuela y Brasil. Estos grupos armados están constituidos por:

  - ELN:

    - 99 municipios 2023, incrementaron accionar 167 municipios (17 deptos.) 2024.
    - Aproximadamente 3.000 guerrilleros (50 % están en territorio venezolano y en la zona fronteriza colombo-venezolana) y grupos de milicias urbanas de apoyo en principales ciudades estructurados a partir de un Comando Central (COCE):
    - Frente de Guerra Central
    - Frente de Guerra Norte.
    - Frente de Guerra Nororiental
    - Frente de Guerra Oriental.
    - Frente de Guerra Occidental
    - Frente de Guerra Darío Ramírez
    - Frente de Guerra Suroccidental (articulación con régimen venezolano).

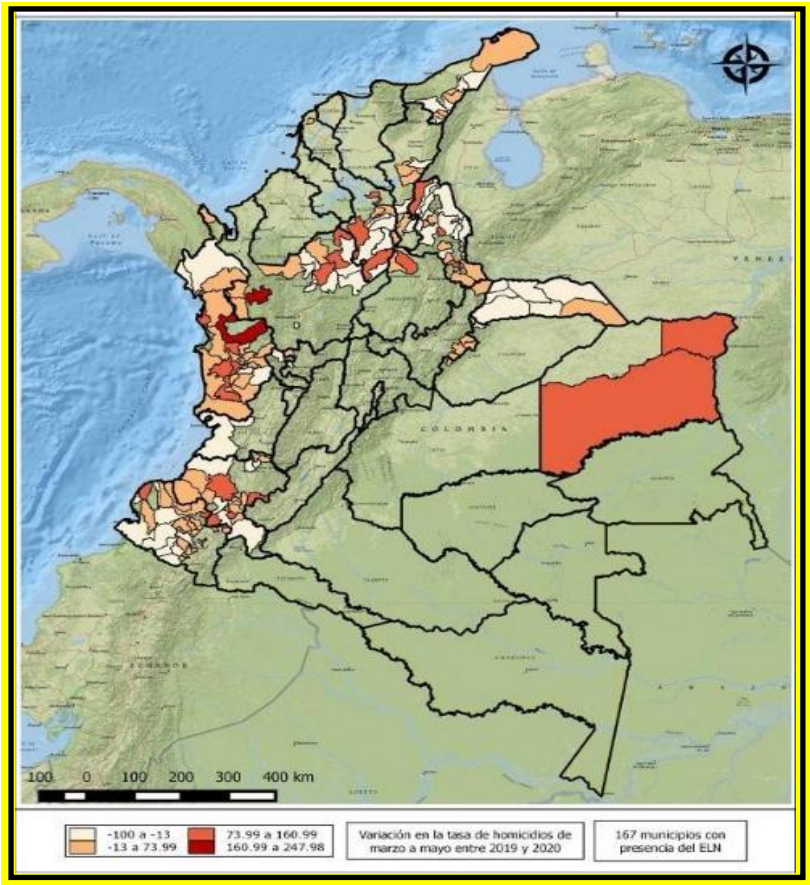

- ## Grupos Armados Post Farc (GAPF):

- 56 municipios 2023, incrementaron su accionar 113 municipios 2024.
- Grupos armados ilegales, residuales de las FARC-EP, que no se adhirieron al Acuerdo de Paz firmado y continúan con actividades ilegales.
- Asociación con carteles mexicanos del narcotráfico.

- ## Clan del Golfo, Caparros y Pelusos:

- Accionar 211 municipios 2023.
- Grupo armado ilegal más grande de Colombia por el enlace entre las diferentes estructuras que le ha permitido un mayor despliegue territorial y accionar delictivo.
- Su enfoque está en la categoría del crimen organizado. Su objetivo central es el enriquecimiento ilícito por la producción y comercialización de la droga con alianza del cartel mexicano de Sinaloa. Aunque esto no es exclusivo de este grupo armado.

2. Ambiente operacional de la seguridad 2021 y delitos de alto impacto.

- La visualización del contexto general anteriormente realizado, obviamente, deberá correlacionarse con un contexto de seguridad más específico. En este sentido, al que más atañe a las operaciones logísticas y de transporte terrestre de carga a nivel nacional. Estos delitos en gran medida son conexos y derivados del ambiente operacional general de la seguridad 2025, especialmente los asociados a la piratería terrestre.

- En general, se observa en estos indicadores que en Colombia durante el 2024 con respecto al 2025, una reducción atípica en los delitos de alto impacto social, sin duda debido al incremento de los actos terroristas determinados por el accionar de los grupos armados ilegales, los cuales se incrementaron significativamente. Este hecho, deberá ser especialmente considerado para las previsiones relacionadas con el ambiente operacional de seguridad 2025. En este sentido, es de prever que, aumentarán los movimientos de protesta y de presión social contra el actual gobierno. Esto muy probablemente materializará interrupciones en las principales rutas nacionales con la presencia de elementos de los grupos armados ilegales que obstaculizarán por lapsos imprevisibles la movilidad del transporte terrestre a de carga a nivel nacional. De hecho, una característica distintiva de los actos terroristas en cuestiónes precisamente la perturbación de la movilidad del transporte terrestre mediante la interrupción del tránsito vehicular por la quema de tractomulas junto con sus mercancías transportadas, la voladura de viaductos, la voladura de oleoductos y el bloqueo de los principales puertos (especialmente Buenaventura y Cartagena) y ciudades capitales departamentales.

- Otro indicador directamente relacionado con la piratería terrestre 2025, muestra la criticidad en los accesos a Bogotá y a las principales ciudades de los Departamentos de Antioquia y del César. Obsérvese el mayor índice en el 1er y 3er trimestre 2025:

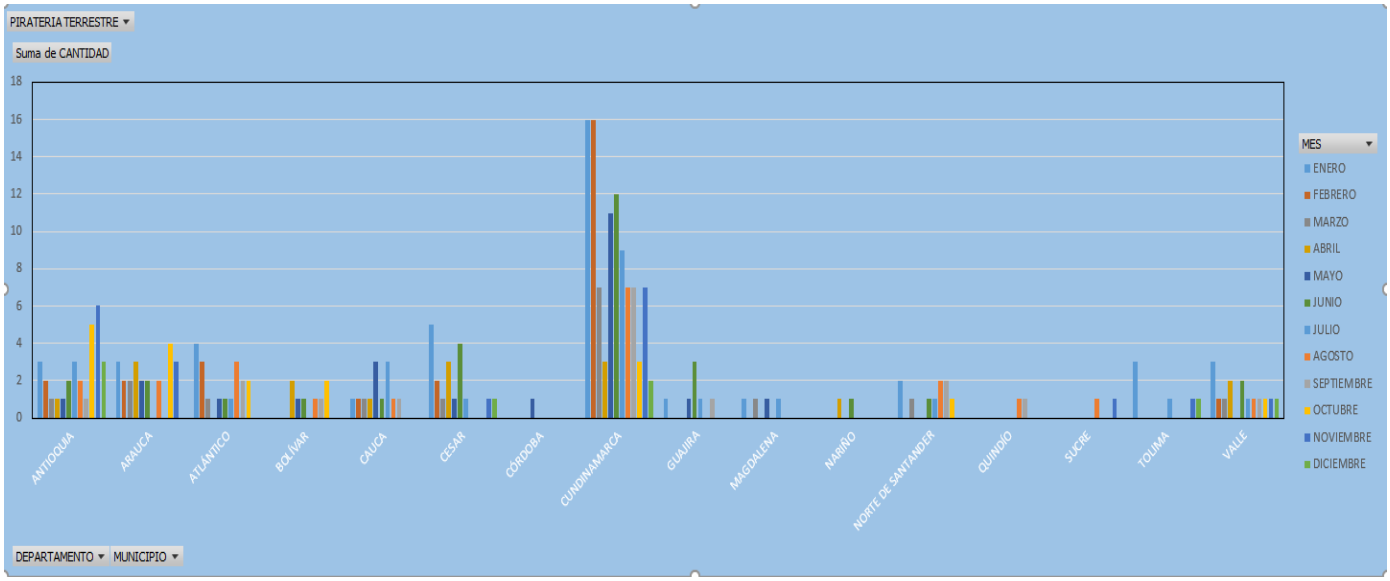

- La observación anterior; a la luz de la gestión de riesgos para el ambiente operacional de seguridad 2021, muestra especialmente la necesidad de mantenery reforzar los esquemas seguridad motorizados y armados para las operaciones de transporte terrestre de carga, principalmente en los accesos urbanos a Bogotá, Medellín y Cartagena.

3. Situación en Buenaventura:

- La violencia en Buenaventura ha recrudecido en los últimos meses producto del enfrentamiento entre grupos ilegales dedicados al comercio ilícito de las drogas que pugnan por el control de las áreas urbanas y su relación con la convergencia de las rutas de la comercialización de las drogas para su salida al exterior. Estos enfrentamientos están acompañados por un aumento significativo de asesinatos selectivos, toques de queda ilegales, extorsión y secuestros en el área urbana de Buenaventura.

- La difícil situación de Buenaventura está directamente vinculada a la disputa entre el Clan del Golfo, estructuras ilegales más pequeñas, ELN y GAPF; y es la que ha provocado la explosión de la violencia generalizada en Buenaventura. De hecho, esta área urbana se ha convertido en una suerte de campo de batalla con tres frentes claramente definidos:

  - El 1ro: entre elementos integrantes del grupo armado ilegal del Clan del Golfo y otras estructuras criminales más pequeñas que no están alineadas con este grupo ilegal y que mantienen cierta independencia de actuación. A este hecho, se suma la llegada de elementos del ELN con intención de incursionar y controlar del casco urbano para disputar la dinámica de la economía ilegal de la droga en Buenaventura y su proyección al exterior; situación que está generando una suerte de reestructuración yredespliegue del Clan del Golfo y de las estructuras criminales más pequeñas.

  - El 2do: la proyección al área urbana de Buenaventura del enfrentamiento sistemático que se ha venido desarrollando entre el grupo armado ilegal del Clan del Golfo y el ELN en las zonas rurales y en el Departamento del Chocó.
  - El 3ro: la llegada de grupos armados Post Farc (GAPF) al escenario geográfico urbano de Buenaventura. Lo anterior, como consecuencia de la convergencia en estaciudad de un estratégico corredor de movilidad que discurre por el Río Nayacontrolado por tres estructuras GAPF:

    - ✓ Columna móvil Jaime Martínez: ejerce control en la parte media alta de los ríos Naya, Yurumanguí y Cajembre.
    - ✓ Frente Unido del Pacífico (estructura residual del antiguo Frente 30 FARC): ejerce control en la afluente baja de los ríos Naya, Yurumanguí y Cajembre; así como también, en los ríos Mayorquín y Raposo.

    - ✓ Frente 29: reforzando al frente anterior y tomando el control de dicha zona.

- Los siguientes mapas visualizan la presencia de los mencionados grupos armados ilegalesen Buenaventura y áreas rurales adyacentes:

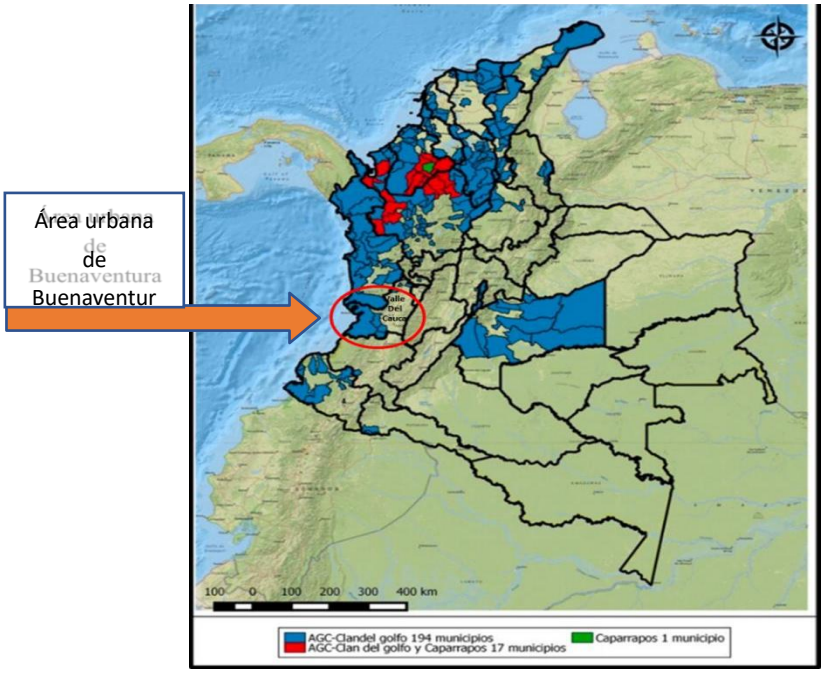

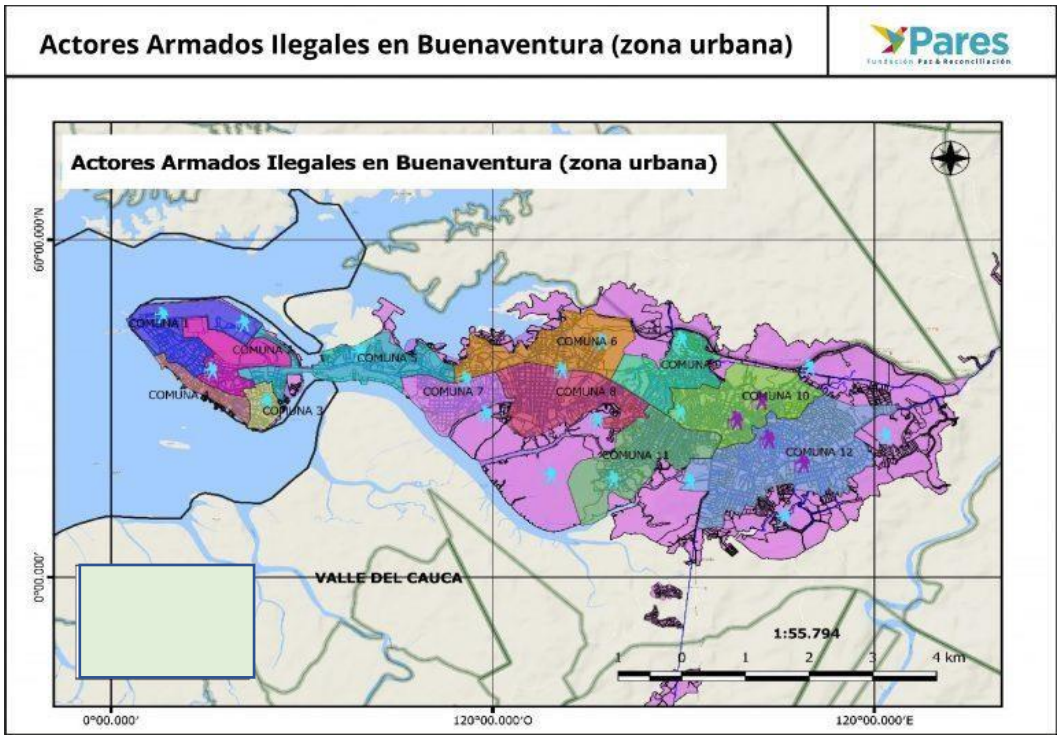

- La situación conflictiva de Buenaventura tiene que ser vista en contexto. La problemática generada por la violencia entre grupos armados ilegales anteriormente descrita, no se circunscribe al área urbana de mencionado puerto. Deberá ser apreciado en su conjunto geográfico. Esto es, la relación que tiene el puerto de Buenaventura no solo con el transporte marítimo y como la puerta principal de Colombia sobre sobre la costa pacífica y el más cercano de todos los puertos a la capital del país y por donde fluye toda la mercancía de importación y exportación hacia y desde el continente asiático.

- Al contexto geoeconómico anterior, se agrega la interconectividad vial terrestre de Buenaventura con la vía Panamericana, y a su vez, con una importante red vial nacional, quizás la mejor del país con el mayor número de kilómetros de autopistas y con muchas de sus vías secundarias y terciarias en buen estado. Esta condición es de fundamental consideración para establecer la relación entre el ambiente operacional de seguridad 2025 analizado y la seguridad de las operaciones logísticas y de transporte terrestre de carga.

- El siguiente mapa visualiza la estratégica interconectividad vial terrestre y portuaria de Buenaventura:

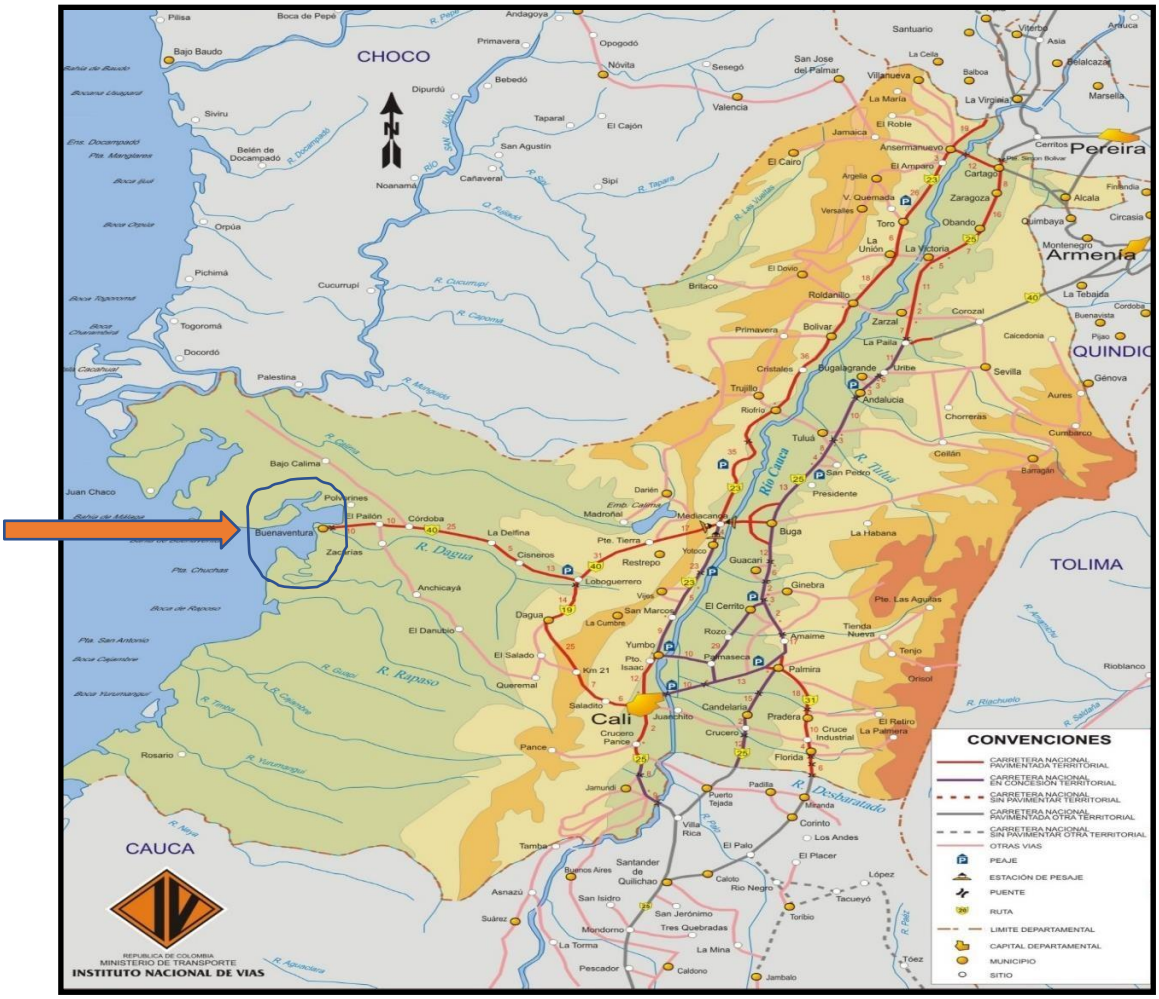

- La situación de violencia en Buenaventura ha de ser minuciosamente considerada por los operadores logísticos y transportadores terrestres de carga por su gran importancia operacional y comercial. La conflictividad por el accionar de grupos armados ilegales y la proximidad de una campaña electoral hace prever complicados escenarios para las operaciones logísticas y de transporte terrestre de carga que impactarán a las zonas portuarias y a la movilidad en los ejes viales en el Valle del Cauca. Tales escenarios, potencialmente presentarán obstáculos por períodos de tiempo imprevisibles generando represamiento de vehículos y del transporte de carga.

4. Situación en la Costa Atlántica:

- La región atlántica ha sido históricamente un área de operaciones de las estructuras del narcotráfico y de los grupos armados ilegales de Colombia. La condición geográfica caribeño atlántica y fronteriza con Venezuela, la convierten en una región estratégica para la exportación de drogas y el ingreso de armas e insumos químicos. Además, conexamente con una tradicional actividad comercial ligada al contrabando y al lavado de activos asociados al tráfico de drogas. Lógicamente, también ha sido el escenario de los múltiples grupos armados ilegales con todo su accionar criminal por el control de las rutas, centros de acopio y puntos de exportación de clorhidrato de cocaína.

- Los puntos geográficos focales lo constituyen las ciudades portuarias de Santa Marta, Barranquilla y Cartagena con gran actividad económica. En un segundo nivel geoeconómico, están las ciudades de Riohacha, Valledupar, Sincelejo y Montería. En general, en los Departamentos de Bolívar, Atlántico, Magdalena, Guajira y Cesar han hecho presencia los siguientes grupos armados ilegales:

  - GAPF:
    - Frente 59: resistencia Wayúu (Sierra Nevada de Santa Marta y Guajira). En la actualidad se encuentra concentrado al norte de la serranía del Perijá.
    - Frente 41: cacique Upar (serranía del Perijá, Cesar). Ubicado en la serranía del Perijá y en el oriente del departamento del Cesar.

  - ELN:
    - Frente José Manuel Martínez Quiroz: presencia en zona rural de los municipios Agustín Codazzi, Becerril, La Jagua de Ibirico, La Paz y San Diego (frontera con Venezuela y serranía del Perijá, Depto. Cesar). Es el único frente activo del ELNen toda la costa norte.
    - Frente Luciano Ariza: presencia en área rural de los municipios Barrancas, El Molino, Fonseca, Urumita y Villanueva. (serranía del Perijá y Depto. Guajira).

- Clan del Golfo:
    - Presencia en la costa atlántica responsables del control y distribución de drogas, cobro de extorsiones y asesinatos selectivos en las áreas urbanas de Cartagena y en los municipios de Turbaco y Santa Rosa de Lima. Mantienen enfrentamientos con los otros grupos armados ilegales por el control de la distribución de estupefacientes, rutas del narcotráfico y extorsión en las mencionadas zonas.

- Los grupos armados ilegales en la costa atlántica han estado relacionados históricamente con políticos activos colombianos. La región no ha sido escenario de grandes cultivos ilícitos, sino más que todo ligada a la criminalidad asociada a la concentración y control de rutas del narcotráfico para la exportación de cocaína.

- El siguiente mapa visualiza la presencia de grupos armados ilegales y el riesgo de actuación criminal en la costa atlántica:

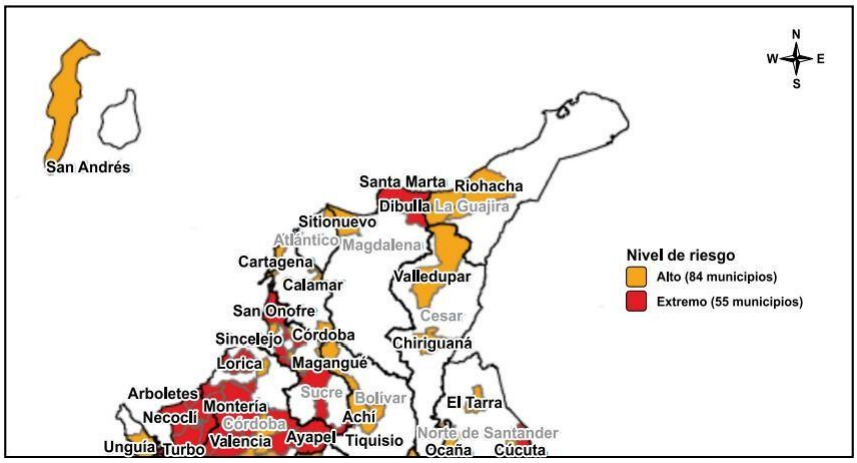

- El ambiente operacional de seguridad 2024 - 2025 en la costa atlántica a los efectos de las operaciones logísticas y de transporte terrestre de carga, luce menos traumático con respecto a la costa del pacífico. Lo riesgos fundamentalmente se centran en la ruta propiamente dicha por eventos asociados a la piratería terrestre común y bloqueos a la vía por parte de las comunidades locales, más que a eventos de carácter terrorista. Esta última situación especialmente en el tramo Aguachica- Curumaní y en el tramo Carmen de Bolívar – Bosconia. La interconectividad estratégica vial terrestre de la costa atlántica se asocia fundamentalmente con la importante red vial nacional de la Ruta del Sol. La probabilidad de bloqueos a las sociedades e instalaciones portuarias en la Costa Atlántica es relativamente baja con respecto a la Costa Pacífica.

- Los siguientes mapas visualizan la interconectividad vial terrestre de la costa atlántica:

La Ruta del Sol

Tramos:

- **Aguachica – Curumaní.**
- **Carmen de Bolívar-Bosconia**.

CONCLUSIONES.

- El centro de gravedad del ambiente operacional de seguridad 2025, lo constituye el accionar delictivo de los grupos armados ilegales vinculados al narcotráfico que operan en Colombia. Esto es, que todo el contexto de la seguridad en Colombia en la actualidadgira en una gran proporción en torno al narcotráfico. Lo anterior, lógicamente en relacióndirecta con la ampliación de las áreas de cultivos ilícitos a nivel nacional y el fortalecimiento de los grupos armados ilegales como consecuencia del Acuerdo de Paz con las FARC. Lo anterior, se ve favorecido exponencialmente por la expansión territorial hacia Venezuela y la articulación operacional de los grupos armados ilegales, especialmente el ELN y GAPF, con el régimen venezolano.

- El ambiente operacional de seguridad 2025, presenta un alto grado de criticidad especialmente en la costa pacífica con respecto a la costa atlántica. En este sentido, Buenaventura es el punto focal de la disputa territorial, operacional y comercial de gruposarmados ilegales Clan del Golfo, ELN, GAPF y estructuras delictivas menores independientes que pugnan por la primacía en las economías ilegales asociadas alnarcotráfico. Es de prever un impacto negativo directo para las operaciones logísticas y de transporte terrestre de carga en esta región con perturbación directa en las zonas portuarias y en las vías de comunicación terrestre. Estas condiciones podrían favorecer la piratería terrestre en menor grado.

- El ambiente operacional de seguridad 2025, en la costa atlántica luce menos conflictivo que en la costa pacífica. Su criticidad está asociada principalmente a actos de piratería terrestre de naturaleza común en los tramos Aguachica- Curumaní y Carmen de Bolívar – Bosconia, más que en las áreas urbanas y portuarias como en Buenaventura. Las características de la infraestructura vial de la denominada Ruta del Sol, minimiza las posibilidades de actos de piratería terrestre en este eje de comunicaciones terrestre.

- El enfoque de gestión de riesgos deberá tener su esfuerzo principal en planes de contingencia en Buenaventura previendo bloqueos a las zonas portuarias y represamientode las operaciones portuarias, y simultáneamente, obstaculización de los principales ejesviales con severo impacto para las operaciones logísticas y de transporte terrestre de carga.

IMPLEMENTACIÓN

Para la fase de implementación y basado en las mejores prácticas del sector y en el contexto de sus procesos de cumplimiento (como las auditorías y la implementación de tecnologías de seguridad), a continuación, se presenta una propuesta estructurada para la organización del proceso de seguridad de YEGO Eco -T.

El objetivo principal es transformar el área de seguridad en un **Sistema de Gestión de Riesgos Integrado (SGR-I)** que proteja a las personas, la carga, los vehículos y la infraestructura, garantizando la continuidad del negocio y el cumplimiento regulatorio.

Misión del Área de Seguridad

Garantizar un entorno operativo seguro y confiable para el transporte de carga, mediante la gestión proactiva de riesgos viales, delictivos y operativos, y el aseguramiento del cumplimiento normativo a nivel nacional e internacional.

Visión del Área de Seguridad

Ser el motor estratégico que posicione a la empresa como un referente nacional en seguridad y confiabilidad en el transporte de carga.

II. Marco Legal y Normativo Clave

El área de seguridad debe garantizar el cumplimiento de las siguientes normativas, que ya se identifican como foco de su gestión:

- **Plan Estratégico de Seguridad Vial (PESV):** Cumplimiento obligatorio de la **Resolución 40595 de 2022** del Ministerio de Transporte, enfocada en la prevención de accidentes de tránsito, la gestión de la flota y el factor humano (conductores).
- **Sistema de Gestión de la Seguridad y Salud en el Trabajo (SG-SST):** Cumplimiento del **Decreto 1079 de 2015** (Sector Transporte) y normas complementarias, con el fin de prevenir accidentes de trabajo y enfermedades laborales.

- **Seguridad en la Cadena de Suministro:** Implementación o mantenimiento de certificaciones como **BASC** con enfoque OEA (Operador Económico Autorizado), que mitigan los riesgos de narcotráfico, contrabando y terrorismo en las operaciones.

III. Estructura Organizacional Propuesta

Se propone una estructura jerárquica con un líder que centralice las funciones de seguridad física, operacional, y de cumplimiento:

Rol Propuesto	Reporta a:	Funciones Clave	Cantidad
Coordinador o encargado del área de seguridad	Gerencia General	Define la política de seguridad, coordina todos los ejes de gestión, es el responsable ante la autoridad y lidera las auditorías de certificación (BASC, ISO, etc.). adicionalmente Gestiona la matriz de riesgos, realiza el estudio de seguridad a los socios de negocio y personal, actualiza la matriz legal, y gestiona los planes de emergencia y continuidad del negocio.	1 (uno) Personal de confianza con disponibilidad 24/7
Analista de trafico y seguridad	**Coordinador o encargado del área de seguridad**	Supervisa la flota en tiempo real, gestiona las alertas GPS, supervisa el cumplimiento del PESV, realiza estudios de seguridad.	4 (cuatro) con Turnos rotativos con cumplimiento de ley

Horario Laboral Central de Trafico:

De acuerdo a lo establecido en la Ley 2101 de 2021 el cual modifico el artículo 161 del código sustantivo del trabajo desde el 15 de Julio de 2025 la duración máxima de la jornada ordinaria de trabajo es de Cuarenta y cuatro (44) horas a la semana y a partir del 15 de Julio de 2026 reducirá dos (2) horas semanales estableciendo una jornada ordinaria de trabajo de Cuarenta y dos (2) horas a la semana. Finalizada la jornada laboral ordinaria, empezaran a regir las horas extras con el respectivo recargo según el turno asignado.

Por ende, se recomienda para una central de Tráfico tener un mínimo de 4 analistas de tráfico y seguridad de Tráfico que laboren en turnos rotativos semanales de 8 horas asegurando la cobertura 24/7 de la operación con un día de descanso en la semana.

Malla de Turnos.

Turno 1: 06:00 – 14:00 horas
Turno 2: 14:00 – 22:00 horas
Turno 3: 22:00 – 06:00 am
Turno 4: 09:00 – 18:00 horas.

FEBRERO																													
CONTROLADOR	1	2	3	4	5	6	7	8	9	10	11	12	13	14	15	16	17	18	19	20	21	22	23	24	25	26	27	28	29
	J	V	S	D	L	M	MI	J	V	S	D	L	M	MI	J	V	S	D	L	M	MI	J	V	S	D	L	M	MI	J
	T4	T4	Des	T7	T3	T3	T3	T3	T8	Des	T5	T1	T1	T1	T1	T1	T5	Des	T2	T2	T2	T2	T2	T6	Des	T4	T4	T4	T4
	T3	T8	Des	T5	T1	T1	T1	T1	T1	T5	Des	T2	T2	T2	T2	T2	T6	Des	T4	T4	T4	T4	T4	Des	T7	T3	T3	T3	T3
	T1	T1	T5	Des	T2	T2	T2	T2	T2	T6	Des	Des	Des	T4	T4	T4	Des	T7	T3	T3	T3	T3	T8	Des	T5	T1	T1	T1	T1
	T2	T2	T6	Des	T4	T4	T4	T4	T4	Des	T7	T3	T3	T3	T3	T8	Des	T5	T1	T1	T1	T1	T1	T5	Des	T2	T2	T2	T2
INCAPACIDAD																													
VACACIONES																													

Turno	Horario
Turno 1	06:00 a 14:00
Turno 2	14:00 a 22:00
Turno 3	22:00 a 06:00
Turno 4	09:00 a 18:00

IV. Ejes de Gestión y Procesos Clave

Los siguientes ejes deben ser los pilares del área, con procedimientos documentados y responsabilidades claras:1. Seguridad Operacional y Vial (PESV)

- **Monitoreo 24/7:** Central de Monitoreo y Control (CMC) para rastreo de vehículos y carga, gestión de alertas y respuesta a emergencias.
- **Tecnología de Flota:** Uso de dispositivos como GPS y plataformas de seguimiento y control en función de evitar y reducir siniestralidad, y cumplir con la Resolución 40595.
- **Gestión de Conductores:** Programas de capacitación continua en manejo defensivo, prevención de fatiga, control de pre operacionales y aplicación de estudios de seguridad periódicos.

2**. Seguridad de la Cadena de Suministro y Física (BASC/OEA)**

- **Gestión de Socios de Negocio:** Fortalecer el proceso de Acuerdo de Seguridad del Asociado de Negocio y el proceso de Conocimiento del Proveedor/Contratista (como se evidencia en sus comunicaciones), solicitando la documentación completa (cámaras de comercio, estados financieros, certificaciones BASC/ISO).

- **Seguridad de la Carga:** Implementación de procedimientos para el control de inventarios de precintos según iso 17712, inspección de contenedores y sellos de seguridad.
- implementación y diseño conceptual de Kpis de seguridad, estudios de seguridad de parqueaderos, matriz de riesgo en ruta, estudios de seguridad de las rutas asociadas a la operación.
- **Seguridad de las Instalaciones:** Control de acceso físico, monitoreo CCTV y gestión de vigilancia de las instalaciones.

3. **Gestión de Riesgos y Cumplimiento**

- **Auditorías Internas/Externas:** Establecer un calendario de auditorías para verificar la efectividad de los controles de seguridad y preparar la renovación de las certificaciones de calidad (ISO) y seguridad (BASC).
- **Planes de Emergencia y Contingencia:** Mantener actualizados y socializados los planes de emergencias y contingencias para responder a incidentes (accidentes, robos, desastres naturales) y asegurar la continuidad de las operaciones.
- **Investigación y Análisis:** Creación de un proceso formal para investigar todos los incidentes de seguridad, determinar las causas raíz y aplicar acciones correctivas y preventivas (como el Plan de Reentrenamiento a personal, o la reevaluación del proceso de selección).

La clave del éxito para su empresa radica en alinear estos ejes de gestión con sus objetivos comerciales, utilizando la **tecnología** y el **cumplimiento normativo** como ventajas competitivas en el mercado colombiano.

Miguel Angel Fernandes Ramos